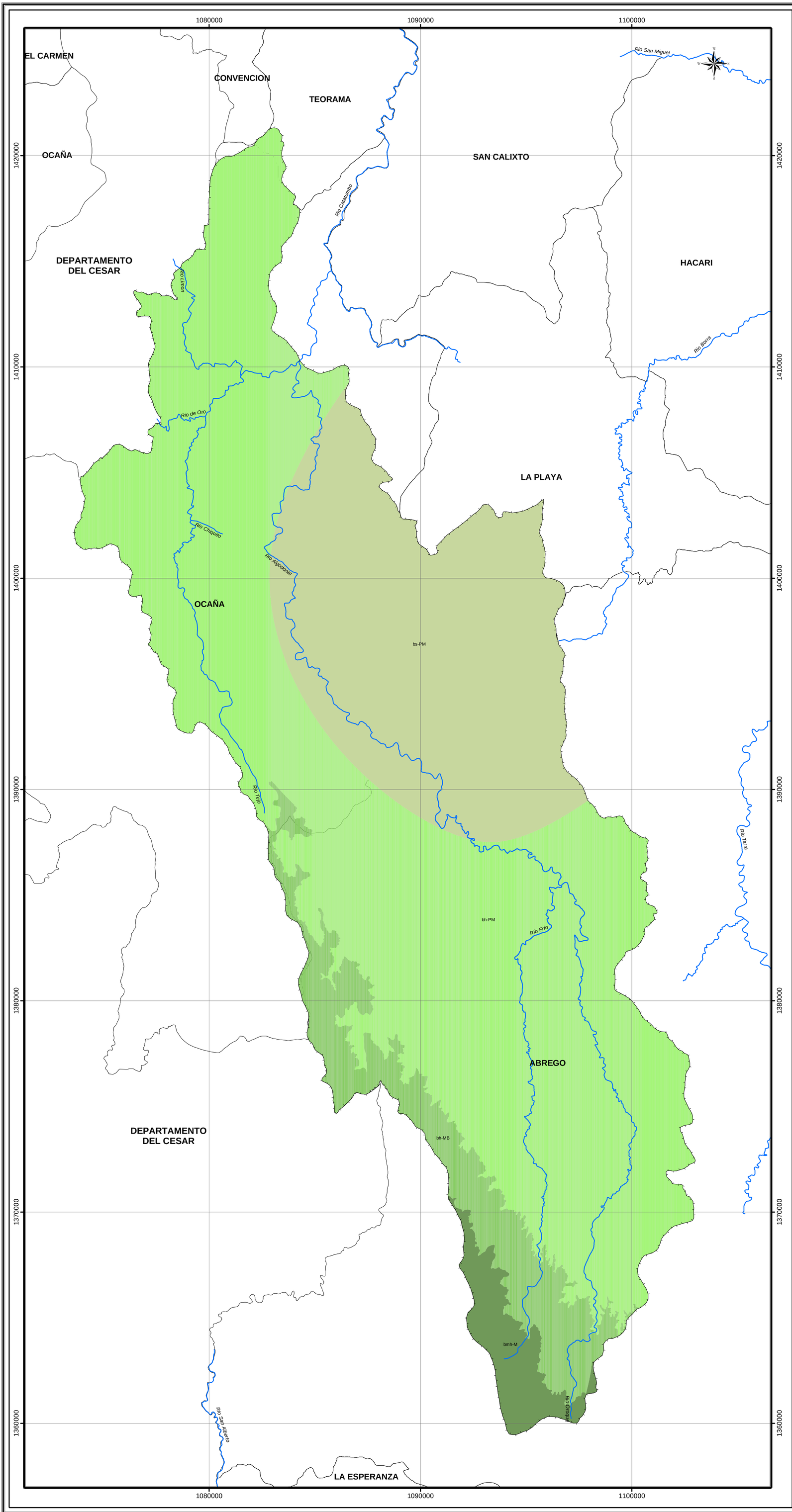

CORPONOR

EN EL FUTURO DE TODOS

MAPA DE ZONAS DE VIDA

Localización

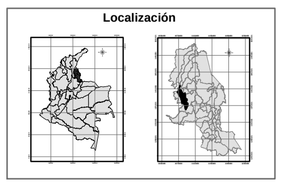

ZONAS DE VIDA SEGÚN HOLDRIDGE	REF.	SIMBOLO	RANGO DE PRECIPITACIÓN (mm)	RANGO ALTITUDINAL (m.s.n.m.)	ÁREA (ha)	% ÁREA
Bosque Muy Humedo Montano		bmh-M	1800-2000	2600-3200	2127,46	3,2
Bosque Humedo Montano Bajo		bh-MB	1900-2000	2000-2600	6109,82	9,2
Bosque Humedo Premontano		bh-PM	1100-1900	1200-2000	47175,05	71,0
Bosque Seco Premontano		bs-PM	788-1000	1200-2000	19226,98	29,0

% ÁREA FORMACIONES VEGETALES O ZONAS DE VIDA SEGÚN HOLDRIDGE EN LA CUENCA DEL RÍO ALGODONAL

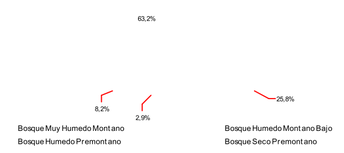

CONVENCIONES

RED HIDROGRÁFICA

Ríos

LÍMITE

Municipal

Cuenca

Elaboró	
Grupo Diagnostico POMCHRA	
Fecha de elaboración: Agosto de 2006	Mapa No: 23

FUENTE	FORMATO	AÑO	ESCALA
Esquema de Ordenamiento Territorial del Municipio La Playa de Belén	DWG	1.999	1 : 50.000
Plan Básico de Ordenamiento Territorial del Municipio de Ábrego	DWG	2.000	1 : 100.000
Plan Básico de Ordenamiento Territorial del Municipio de Ocaña	DWG	2.002	1 : 50.000
Plan de Ordenamiento y Manejo Ambiental de la Cuenca Alta del Río Catatumbo	DWG	1.997	1 : 50.000
IGAG Estudio General de Suelos de Norte de Santander	DWG	2.004	1 : 100000

Fuente de la información de cartografía base dígital tomada POT´s planchas IGAC 1:25000

Metodología de uso y cobertura basada en la "Unificación en la leyenda de clasificación de la cobertura y uso de la tierra para el departamento de Norte de Santander" SIAT-CORPONOR

Ecosistemas de los Andes, Instituto Alexander Von Humboldt

REFERENCIA ESPACIAL

Elipsoide: Internacional 1909
Origen: Observatorio Astronómico de Bogotá
Proyección: Gauss Krugger
Coordenadas Planas: 1.000.000 metros Norte
1.000.000 metros Este

ESCALA GRÁFICA
1 : 100.000

2000 0 8000

Metros